MANUEL DE USUARIO DEL SISTEMA DE REGISTRO DE MINUTAS EN EL DEPARTAMENTO DE GESTIÓN DE RIESGOS YA ADMINISTRACIÓN DE DESASTRES

Protección Civil y Administración de Desastres Municipal – Edif. Protección Civil Municipal, Calle Rosales, Sector Palotal, Detrás del Ambulatorio Ali Romero, Frente a la Circunscripción Militar del Estado Anzoátegui – Barcelona Edo Anzoátegui.
Teléfono: 02812770791 / Correo: pcadm.bolivar@gmail.com / pcbolivar.riesgos@gmail.com

Indice:

1. Introducción 4
1.1. Propósito del Sistema 4
1.2. Acceso al Sistema 4
2. Instalación y Configuración Inicial (Para Administradores/Desarrolladores) 4
2.1. Requisitos del Sistema 4
2.2. Instalación de Node.js 4
2.3. Instalación de MongoDB 5
2.4. Instalación del Proyecto (Backend y Frontend) 7
2.5. Ejecución del Servidor de Desarrollo 8
3. Interfaz de Usuario y Primeros Pasos 9
3.1. Inicio de Sesión 9
3.2. Navegación Principal 10
3.3. Cierre de Sesión 10
4. Gestión de Puntos de Riesgo (Marcas) 10
4.1. Creación de un Nuevo Punto de Riesgo (Marca) 10
4.2. Visualización de Puntos en el Mapa 11
4.3. Información Detallada de un Punto de Riesgo 12
5. Gestión de Minutas (Reportes) 13
5.1. ¿Qué es una Minuta? 13
5.2. Creación de una Minuta desde un Punto de Riesgo 13
5.3. Edición de una Minuta 13
6. Configuración del Sistema 14
6.1. Acceso al Panel de Configuración 14
6.2. Configuración de Usuarios y Roles 14
6.2.1. Creación de un Nuevo Usuario 15
6.2.2. Gestión de Usuarios Existentes 15
6.3. Editor de Roles 15
6.3.1. Modificar un Rol 15
6.3.2. Asignación de Permisos 16
6.4. Listas y Datos Seleccionables 16
6.4.1. Orígenes (Grupos de Listas) 17

Protección Civil y Administración de Desastres Municipal – Edif. Protección Civil Municipal, Calle Rosales, Sector Palotal, Detrás del Ambulatorio Ali Romero, Frente a la Circunscripción Militar del Estado Anzoátegui – Barcelona Edo Anzoátegui.
Teléfono: 02812770791 / Correo: pcadm.bolivar@gmail.com / pcbolivar.riesgos@gmail.com

6.4.2. Gestión de Empleados 18
6.5. Editor de Plantillas de Minuta 19
6.5.1. Creación de una Nueva Plantilla 19
6.5.2. Configuración de Campos de Plantilla 19
7. Generador de Estadísticas y Reportes 20
7.1. Acceso al Panel de Estadísticas 20
7.2. Resumen General y Ranking 20
7.3. Línea del Tiempo y Filtros 21
7.4. Estadísticas General y Avanzado 21
7.5. Análisis de Costos (Sumatoria y Promedio) 22
7.6. Tablas Recopilatorias de Minutas 22
7.7.Reporte General y Avanzado 23

Protección Civil y Administración de Desastres Municipal – Edif. Protección Civil Municipal, Calle Rosales, Sector Palotal, Detrás del Ambulatorio Ali Romero, Frente a la Circunscripción Militar del Estado Anzoátegui – Barcelona Edo Anzoátegui.
Teléfono: 02812770791 / Correo: pcadm.bolivar@gmail.com / pcbolivar.riesgos@gmail.com

1. Introducción

1.1. Propósito del Sistema

Este sistema es una herramienta de gestión de información georreferenciada diseñada para reportar, dar seguimiento y analizar puntos de riesgo. Permite a los usuarios crear "marcas" en un mapa, asociarles "minutas" (reportes detallados), gestionar usuarios y roles, y generar estadísticas avanzadas para la toma de decisiones.

1.2. Acceso al Sistema

El sistema es una aplicación web. Una vez instalado y en ejecución, se accede a través de un navegador web (como Chrome, Edge o Firefox) ingresando la dirección (URL) donde está alojado.

· Para desarrollo local: La dirección suele ser http://localhost:4040 (como se ve en las imágenes de instalación) o la IP de la máquina que lo ejecuta (ej. http://192.168.1.4:4040).

2. Instalación y Configuración Inicial (Para Administradores/Desarrolladores)

2.1. Requisitos del Sistema

· Sistema Operativo: Windows
· Node.js: Versión 18 o superior (incluye npm).
· MongoDB: Versión 8.2 o superior.
· Navegador Web: Actualizado.

2.2. Instalación de Node.js

1. Ejecuta el instalador de Node.js.
2. En la ventana "Destination Folder", puedes dejar la ruta por defecto (C:\Program Files\nodejs\) o hacer clic en "Change..." para seleccionar otra ubicación.
3. Haz clic en "Next" y luego en "Install" para completar la instalación.

Protección Civil y Administración de Desastres Municipal – Edif. Protección Civil Municipal, Calle Rosales, Sector Palotal, Detrás del Ambulatorio Ali Romero, Frente a la Circunscripción Militar del Estado Anzoátegui – Barcelona Edo Anzoátegui.
Teléfono: 02812770791 / Correo: pcadm.bolivar@gmail.com / pcbolivar.riesgos@gmail.com

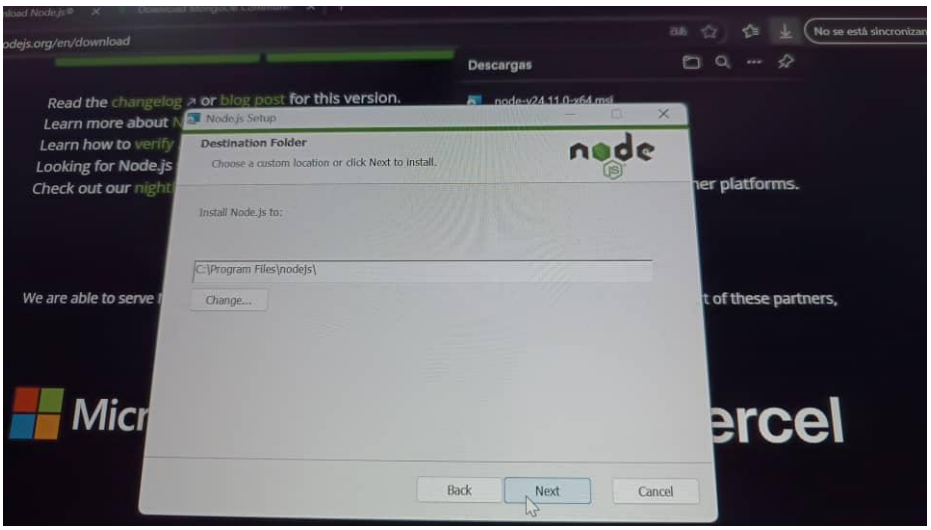

2.3. Instalación de MongoDB

1. Ejecuta el instalador de MongoDB
2. Haz clic en "Next" para comenzar.

3. En la ventana "Custom Setup", puedes dejar la ubicación por defecto (C:\Program Files\MongoDB\Server\8.2\) o cambiarla con el botón "Browse...". Asegúrate de que todas las características estén seleccionadas para su instalación. Haz clic en "Next"

Protección Civil y Administración de Desastres Municipal – Edif. Protección Civil Municipal, Calle Rosales, Sector Palotal, Detrás del Ambulatorio Ali Romero, Frente a la Circunscripción Militar del Estado Anzoátegui – Barcelona Edo Anzoátegui.
Teléfono: 02812770791 / Correo: pcadm.bolivar@gmail.com / pcbolivar.riesgos@gmail.com

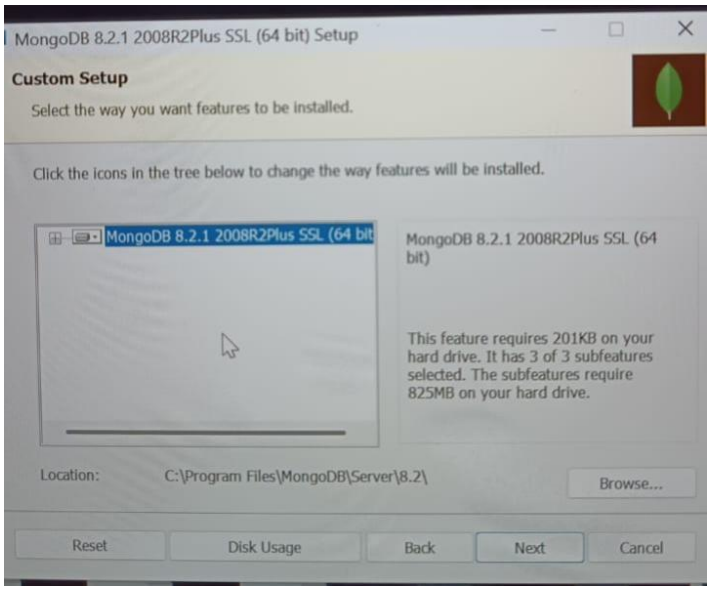

4. En la ventana "Service Configuration", configura MongoDB como un servicio de Windows para que se inicie automáticamente:

· Marca "Install MongoDB as a Service".
· Se recomienda "Run service as Network Service user".
· Puedes personalizar el "Service Name" si lo deseas (por defecto "MongoDB").
· Confirma o cambia los directorios para los datos y los logs.
· Haz clic en "Next"

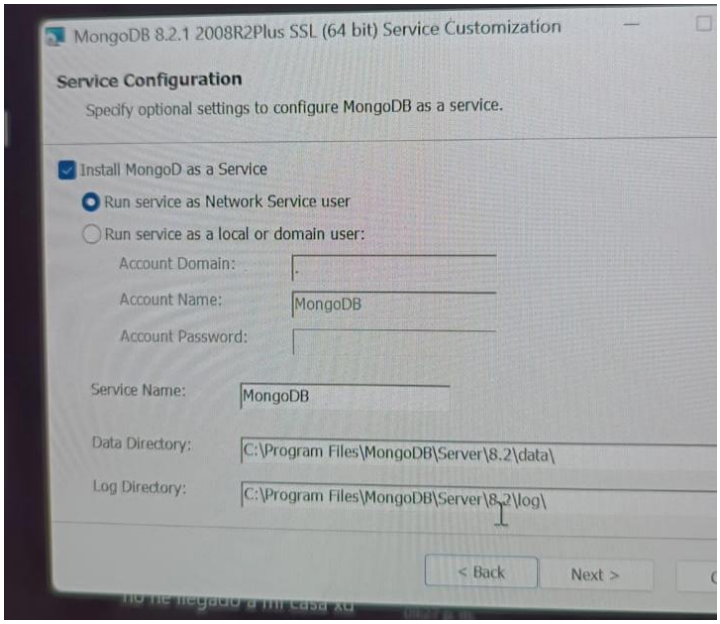

5. Haz clic en "Install" para completar el proceso.

Protección Civil y Administración de Desastres Municipal – Edif. Protección Civil Municipal, Calle Rosales, Sector Palotal, Detrás del Ambulatorio Ali Romero, Frente a la Circunscripción Militar del Estado Anzoátegui – Barcelona Edo Anzoátegui.
Teléfono: 02812770791 / Correo: pcadm.bolivar@gmail.com / pcbolivar.riesgos@gmail.com

2.4. Instalación del Proyecto (Backend y Frontend)

1. Abre una terminal como administrador (Símbolo del sistema o PowerShell).
2. Navega hasta la carpeta donde se encuentra el proyecto descargado. Por ejemplo:

```
cd C:\Users\HP\Downloads\proyecto-ingenieria-master\proyecto-ingenieria-master
```

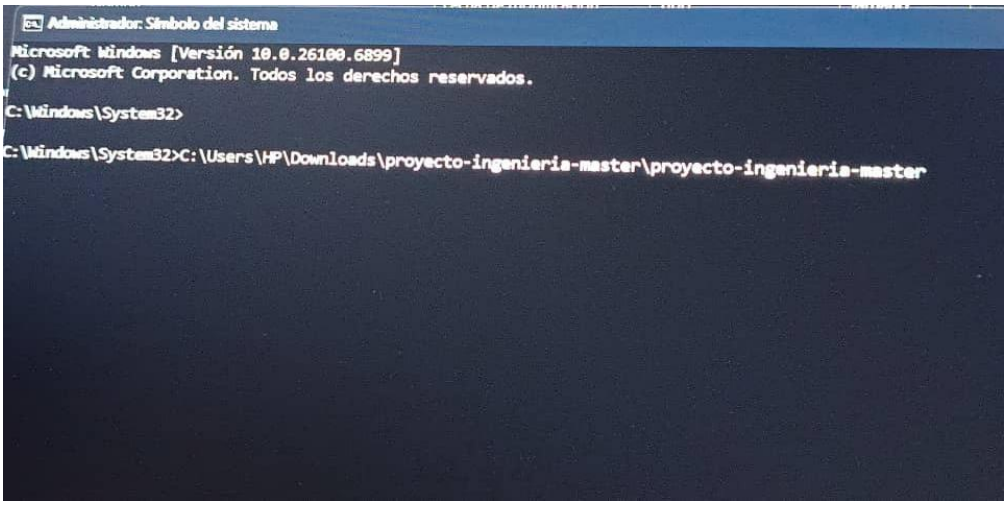

· Nota: Si ves un error como "El sistema no puede encontrar la ruta especificada", verifica que la ruta sea correcta. En la siguiente imagen el usuario escribió "WP" en lugar de "HP".

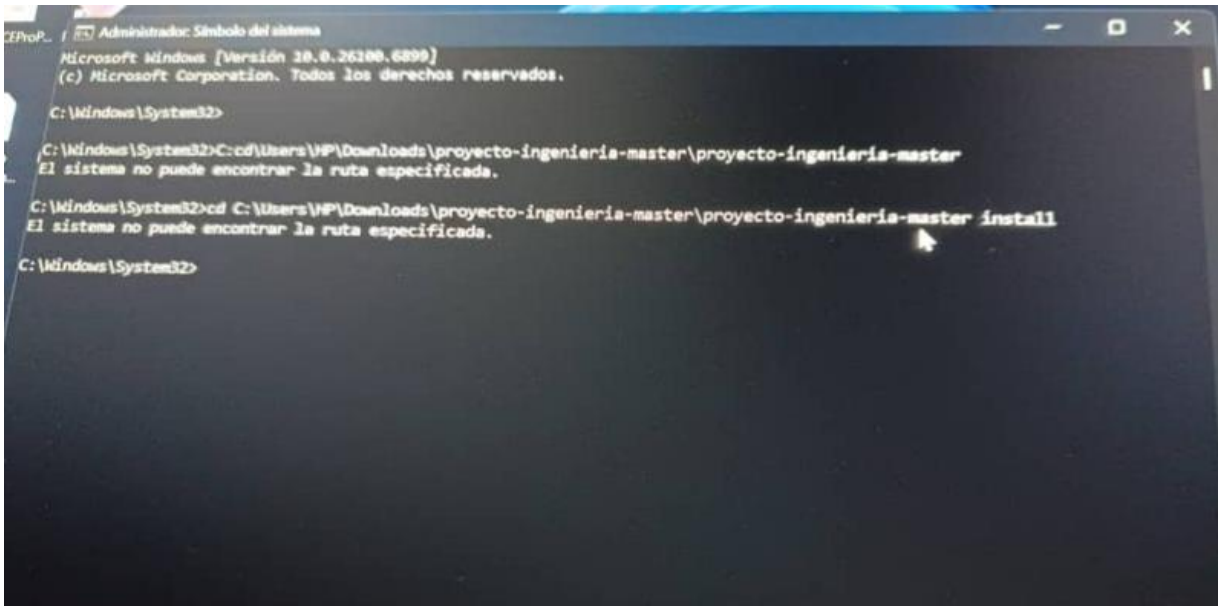

3. Una vez dentro de la carpeta del proyecto, ejecuta el siguiente comando para instalar todas las dependencias necesarias (listadas en el archivo package.json):

Protección Civil y Administración de Desastres Municipal – Edif. Protección Civil Municipal, Calle Rosales, Sector Palotal, Detrás del Ambulatorio Ali Romero, Frente a la Circunscripción Militar del Estado Anzoátegui – Barcelona Edo Anzoátegui.
Teléfono: 02812770791 / Correo: pcadm.bolivar@gmail.com / pcbolivar.riesgos@gmail.com

npm install

· Durante este proceso, es posible que veas advertencias (warnings) o vulnerabilidades. Es normal. Al final, se mostrará un resumen. Si hay vulnerabilidades, puedes intentar corregirlas con los comandos que sugiere el sistema (npm audit fix), como se muestra en las siguiente imagen.

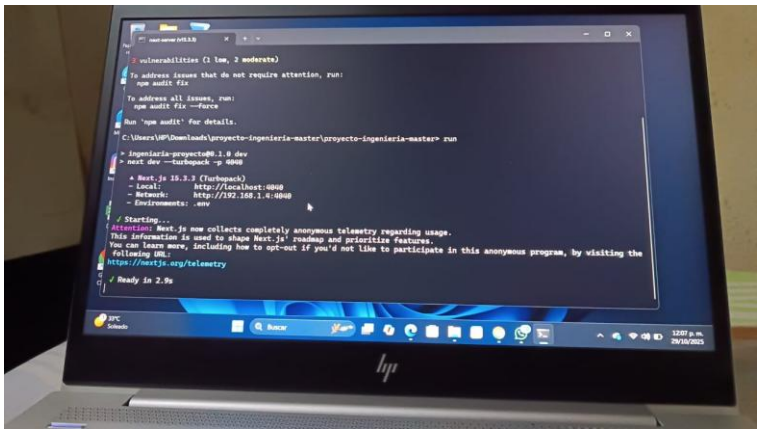

2.5. Ejecución del Servidor de Desarrollo

1. Una vez finalizada la instalación de dependencias, ejecuta el siguiente comando para iniciar la aplicación en modo de desarrollo:

npm run dev

2. Si el firewall de Windows lo solicita, haz clic en "Permitir" para que la aplicación pueda comunicarse en la red.

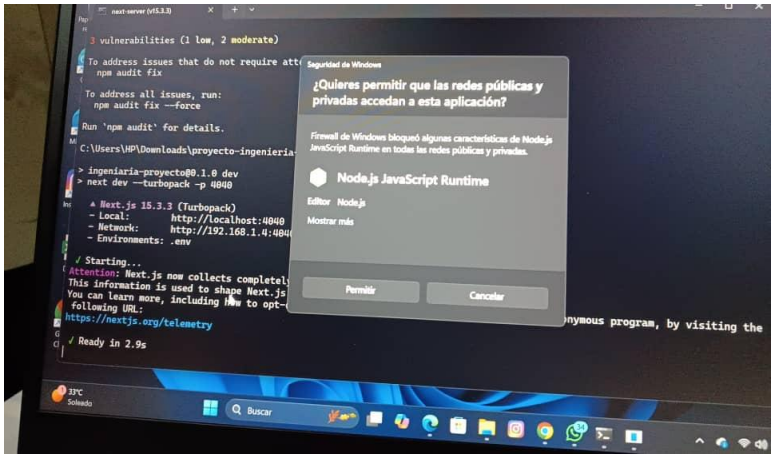

3. Verás en la terminal un mensaje similar a:

A Next.js 15.3.3 (Turbopack)
- Local: http://localhost:4040

Protección Civil y Administración de Desastres Municipal – Edif. Protección Civil Municipal, Calle Rosales, Sector Palotal, Detrás del Ambulatorio Ali Romero, Frente a la Circunscripción Militar del Estado Anzoátegui – Barcelona Edo Anzoátegui.
Teléfono: 02812770791 / Correo: pcadm.bolivar@gmail.com / pcbolivar.riesgos@gmail.com

- Network: http://192.168.1.4:4040

Esto indica que el servidor se ha iniciado correctamente.

4. Abre tu navegador y ve a http://localhost:4040 para acceder a la aplicación.

3. Interfaz de Usuario y Primeros Pasos

3.1. Inicio de Sesión

1. Al abrir la aplicación por primera vez, verás la pantalla de "Iniciar sesión" (IMG-20251029-WA0046.jpg).

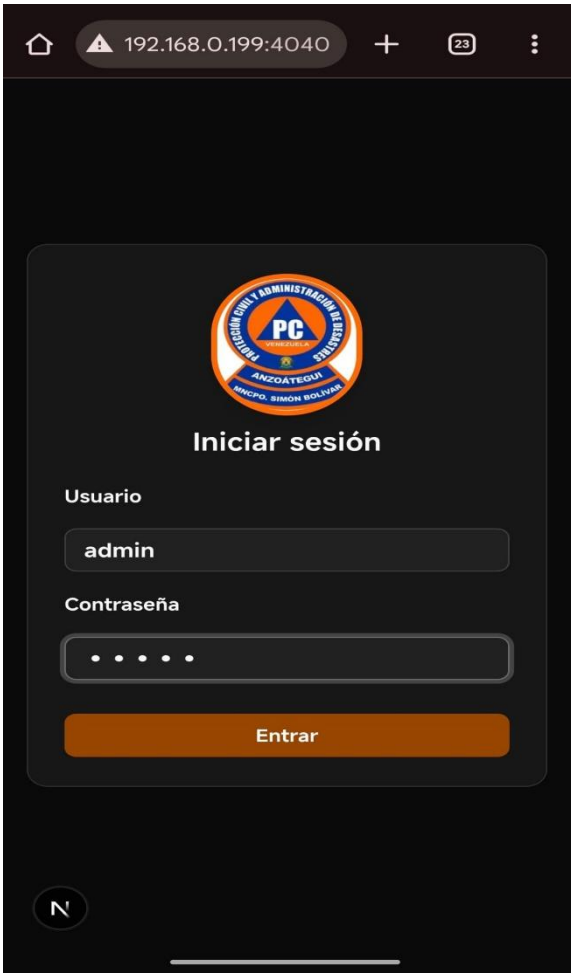

2. Ingresa tus credenciales:
   · Usuario: (Ej. admin)
   · Contraseña: (Ej. .....)
3. Haz clic en el botón "Entrar".

Protección Civil y Administración de Desastres Municipal – Edif. Protección Civil Municipal, Calle Rosales, Sector Palotal, Detrás del Ambulatorio Ali Romero, Frente a la Circunscripción Militar del Estado Anzoátegui – Barcelona Edo Anzoátegui.
Teléfono: 02812770791 / Correo: pcadm.bolivar@gmail.com / pcbolivar.riesgos@gmail.com

3.2. Navegación Principal

Una vez dentro, la interfaz principal (dashboard) te dará la bienvenida. En ella podrás ver:

· Un buscador en la parte superior
· Un botón para "Cerrar sesión" en la esquina superior derecha.
· Accesos a los diferentes módulos del sistema, que se detallan en este manual.

3.3. Cierre de Sesión

Para salir de la plataforma de forma segura, haz clic en el botón "Cerrar sesión" ubicado en la parte superior derecha de la pantalla en la siguiente imagen se puede observar estos campos.

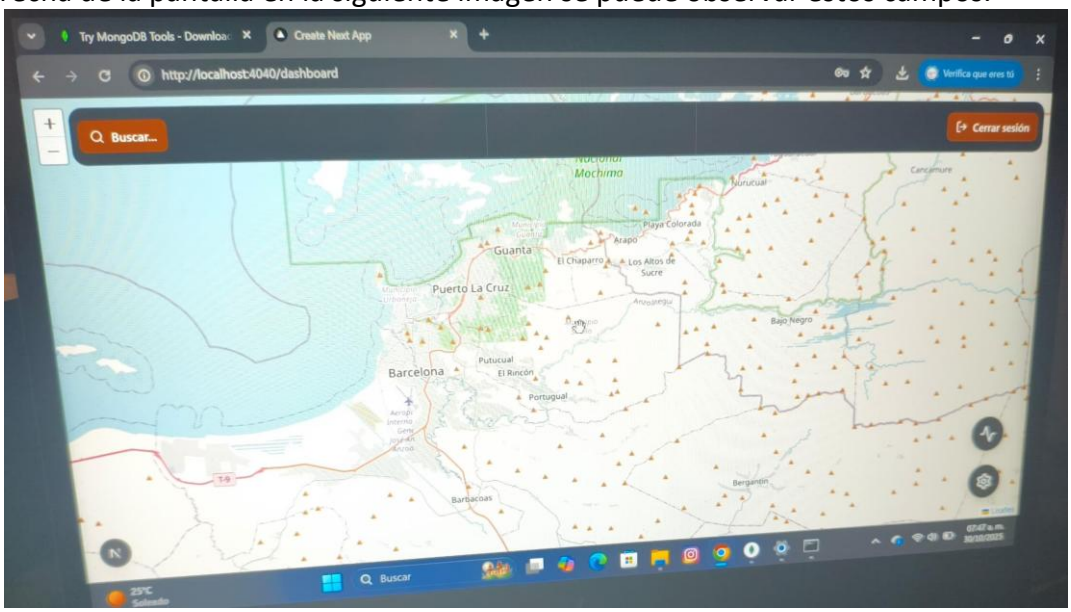

4. Gestión de Puntos de Riesgo (Marcas)

4.1. Creación de un Nuevo Punto de Riesgo (Marca)

1. Desde el mapa principal o la sección correspondiente, busca la opción para "Crea una marca" presionando clip derecho.
2. Se abrirá un formulario. Completa los campos:
   · Asunto: Un título para el punto de riesgo (ej. "Prueba1").
   · Descripción: Una breve descripción del riesgo (ej. "aaa").
   · Punto de referencia: Un lugar cercano conocido para ubicarlo fácilmente (ej. "referencia 1").
3. La ubicación en el mapa se selecciona generalmente haciendo clic en el lugar deseado. Las coordenadas (Lat, Lng) se capturarán automáticamente.

Protección Civil y Administración de Desastres Municipal – Edif. Protección Civil Municipal, Calle Rosales, Sector Palotal, Detrás del Ambulatorio Ali Romero, Frente a la Circunscripción Militar del Estado Anzoátegui – Barcelona Edo Anzoátegui.
Teléfono: 02812770791 / Correo: pcadm.bolivar@gmail.com / pcbolivar.riesgos@gmail.com

4. Haz clic en "Guardar" para crear la marca. También tienes la opción "Cancel" para descartar la operación.

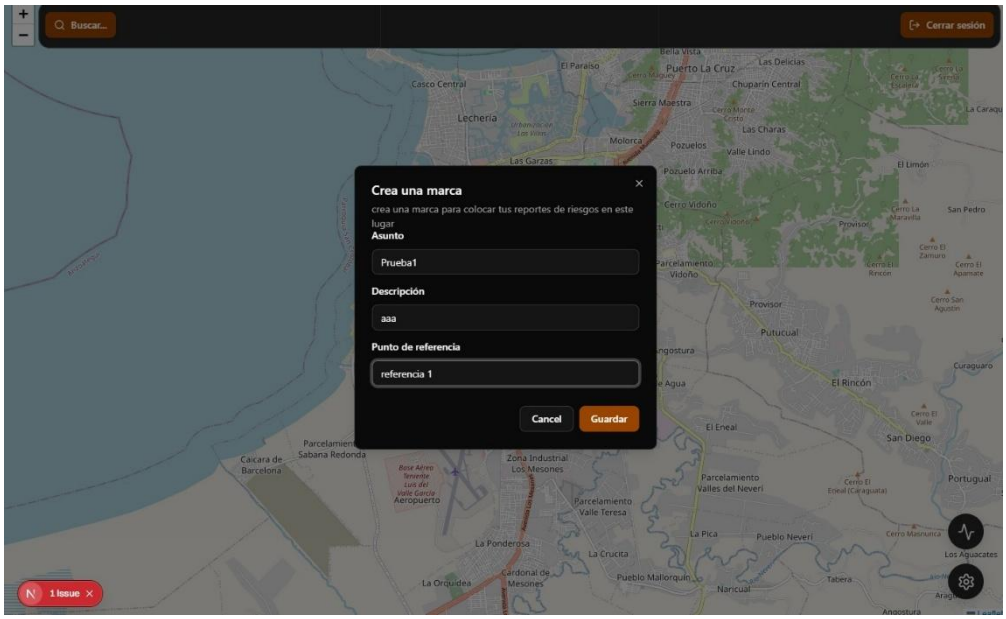

4.2. Visualización de Puntos en el Mapa

En el panel principal del mapa, podrás ver todos los puntos de riesgo creados representados como marcadores. Al hacer clic en uno, se desplegará información básica.

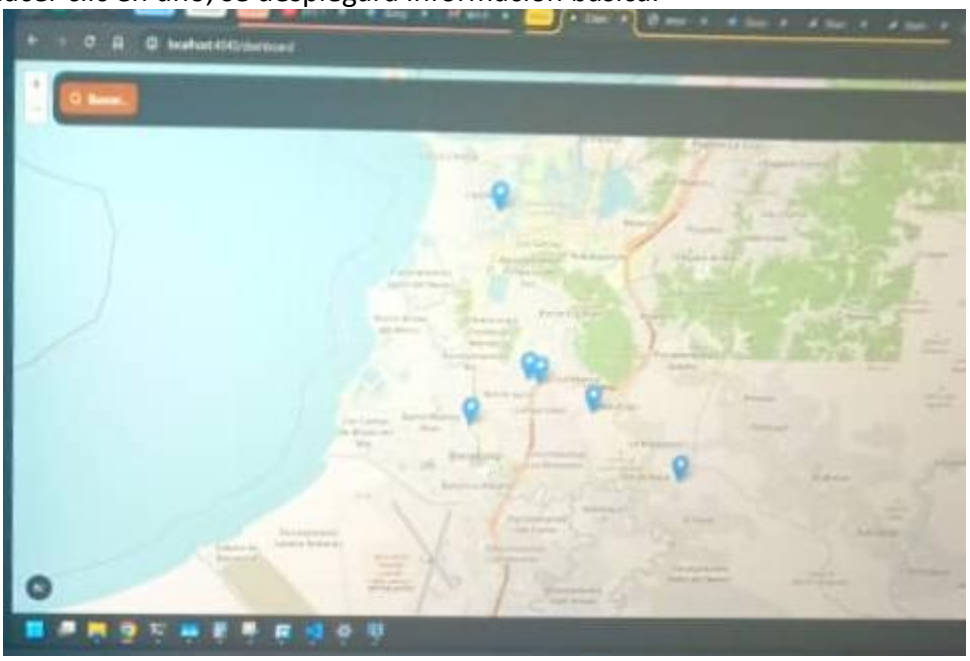

Protección Civil y Administración de Desastres Municipal – Edif. Protección Civil Municipal, Calle Rosales, Sector Palotal, Detrás del Ambulatorio Ali Romero, Frente a la Circunscripción Militar del Estado Anzoátegui – Barcelona Edo Anzoátegui.
Teléfono: 02812770791 / Correo: pcadm.bolivar@gmail.com / pcbolivar.riesgos@gmail.com

4.3. Información Detallada de un Punto de Riesgo

Al hacer clic en un marcador del mapa, se abrirá una ventana de información Esta ventana muestra:

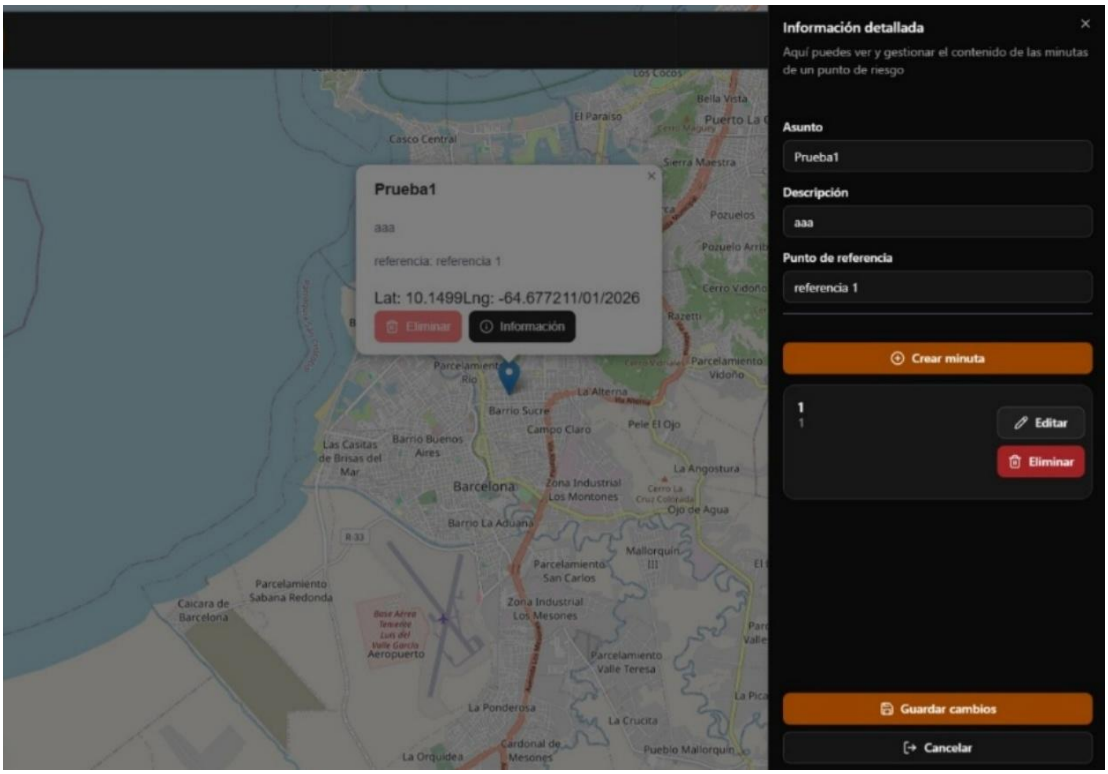

· El Asunto del punto (ej. "Prueba1").
· La Descripción (ej. "aaa").
· El Punto de referencia (ej. "referencia_1").
· Las coordenadas geográficas (Latitud y Longitud) y la fecha de creación.
· Botones de acción:
  · [Información]: Te lleva a la vista detallada del punto.
  · [Eliminar]: Borra el punto de riesgo del sistema.

En la vista de "Información detallada", además de ver la información del punto, encontrarás:

· Una lista de "Puntos de interés" cercanos o relacionados (ej. "Barrio Sucre", "Campo Claro", etc.). Esto podría ser una lista seleccionable para asociar al punto.
· Botones para "Crear minuta", "Editar" el punto, o "Eliminar" lo.
· Opciones para "Guardar cambios" o "Cancelar" después de una edición.

Protección Civil y Administración de Desastres Municipal – Edif. Protección Civil Municipal, Calle Rosales, Sector Palotal, Detrás del Ambulatorio Ali Romero, Frente a la Circunscripción Militar del Estado Anzoátegui – Barcelona Edo Anzoátegui.
Teléfono: 02812770791 / Correo: pcadm.bolivar@gmail.com / pcbolivar.riesgos@gmail.com

5. Gestión de Minutas (Reportes)

5.1. ¿Qué es una Minuta?

Una minuta es un reporte o informe detallado asociado a un punto de riesgo específico. Puede contener información como títulos, descripciones, costos, y campos personalizados definidos por una plantilla.

5.2. Creación de una Minuta desde un Punto de Riesgo

1. Accede a la "Información detallada" de un punto de riesgo.
2. Haz clic en el botón "Crear minuta"
3. Serás dirigido a un formulario para crear la minuta

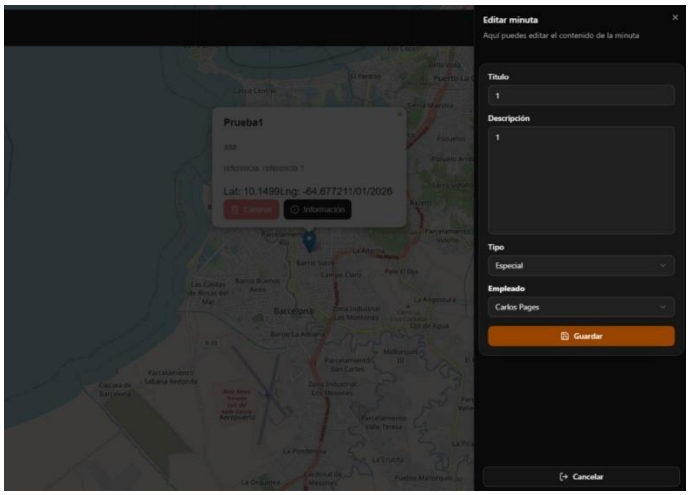

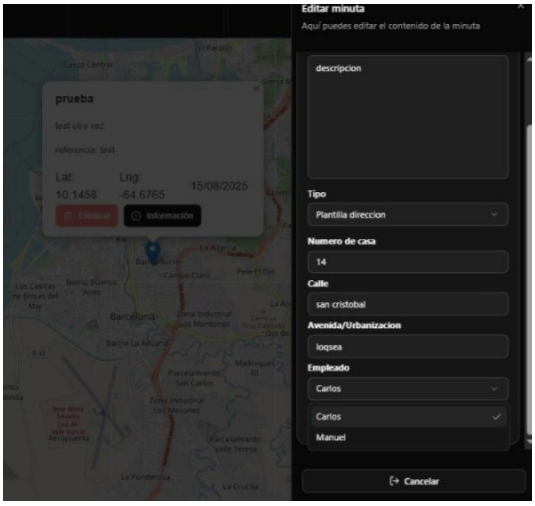

Aquí podrás:
· Escribir un "Título".
· Añadir una "Descripción".
· Seleccionar un "Tipo" de minuta (ej. "Especial", "Plantilla dirección"). Los tipos se configuran en el panel de administración.
· Seleccionar un "Empleado" responsable de la minuta de una lista desplegable.
· Completar otros campos que la plantilla seleccionada pueda requerir (ej. "Numero de casa", "Calle", "Avenida/Urbanización", como se ve en IMG-20251025-WA0017.jpg).
4. Haz clic en "Guardar" para crear la minuta.

5.3. Edición de una Minuta

Para modificar una minuta existente:

Protección Civil y Administración de Desastres Municipal – Edif. Protección Civil Municipal, Calle Rosales, Sector Palotal, Detrás del Ambulatorio Ali Romero, Frente a la Circunscripción Militar del Estado Anzoátegui – Barcelona Edo Anzoátegui.
Teléfono: 02812770791 / Correo: pcadm.bolivar@gmail.com / pcbolivar.riesgos@gmail.com

1. Navega hasta la vista de edición, probablemente desde la tabla de minutas o desde el punto de riesgo asociado.
2. En la pantalla "Editar minuta" (siguiendo las imágenes que se muestra en el 5.2), podrás cambiar el contenido de todos los campos: Título, Descripción, Tipo, Empleado, y cualquier otro campo específico de la plantilla.
3. Después de realizar los cambios, haz clic en el botón "Guardar".

6. Configuración del Sistema

6.1. Acceso al Panel de Configuración

Desde el panel principal, busca y haz clic en el engranaje el cual despliega la opción "Configuraciones" Aquí se gestionan todos los aspectos del sistema.

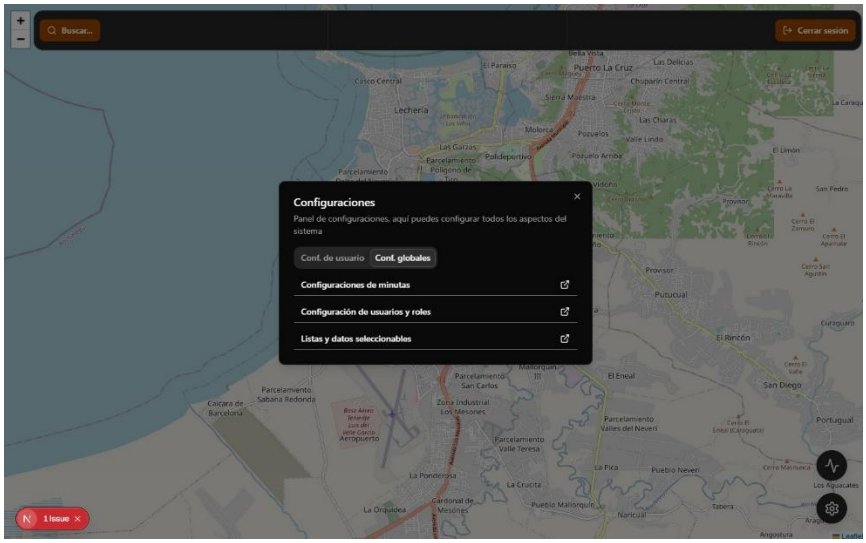

Dentro de las configuraciones globales, encontrarás tres módulos principales:

· Configuración de minutas
· Configuración de usuarios y roles
· Listas y datos seleccionables

6.2. Configuración de Usuarios y Roles

Esta sección, llamada "Usuarios de la plataforma", permite gestionar quién puede acceder al sistema y qué puede hacer.

Protección Civil y Administración de Desastres Municipal – Edif. Protección Civil Municipal, Calle Rosales, Sector Palotal, Detrás del Ambulatorio Ali Romero, Frente a la Circunscripción Militar del Estado Anzoátegui – Barcelona Edo Anzoátegui.
Teléfono: 02812770791 / Correo: pcadm.bolivar@gmail.com / pcbolivar.riesgos@gmail.com

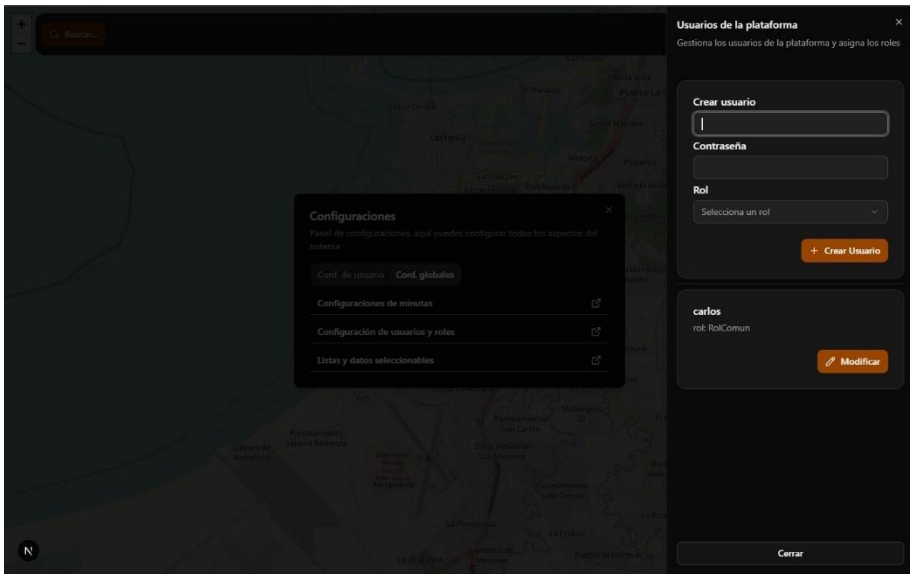

6.2.1. Creación de un Nuevo Usuario

1. En el panel "Usuarios de la plataforma", localiza el formulario "Crear usuario".
2. Ingresa el nombre de usuario.
3. Ingresa una contraseña.
4. En el desplegable "Rol", selecciona el rol que se le asignará (ej. "RolComun").
5. Haz clic en el botón "+ [Crear Usuario]" para añadirlo a la plataforma.

6.2.2. Gestión de Usuarios Existentes

La lista de usuarios muestra los ya creados, como "Carlos" con el rol "RolComun". Junto a cada usuario hay un botón "Modificar" para editar su información o cambiar su rol como se muestra en la imagen anterior.

6.3. Editor de Roles

Al hacer clic en "Modificar" un rol (o desde una opción dedicada), accedes al "Editor de roles"

6.3.1. Modificar un Rol

En esta pantalla puedes ver y editar la información de un rol específico:

· codename: El identificador único interno del rol (ej. "rolcomun").
· Título: El nombre visible del rol (ej. "RolComun").
· Deshabilitado: Una casilla de verificación para activar o desactivar el rol. Si está marcada, los usuarios con este rol no podrán usar el sistema.

Protección Civil y Administración de Desastres Municipal – Edif. Protección Civil Municipal, Calle Rosales, Sector Palotal, Detrás del Ambulatorio Ali Romero, Frente a la Circunscripción Militar del Estado Anzoátegui – Barcelona Edo Anzoátegui.
Teléfono: 02812770791 / Correo: pcadm.bolivar@gmail.com / pcbolivar.riesgos@gmail.com

· Botón "Guardar" para aplicar los cambios.

6.3.2. Asignación de Permisos

La sección más importante es "Permisos". Aquí se definen las acciones que los usuarios con este rol

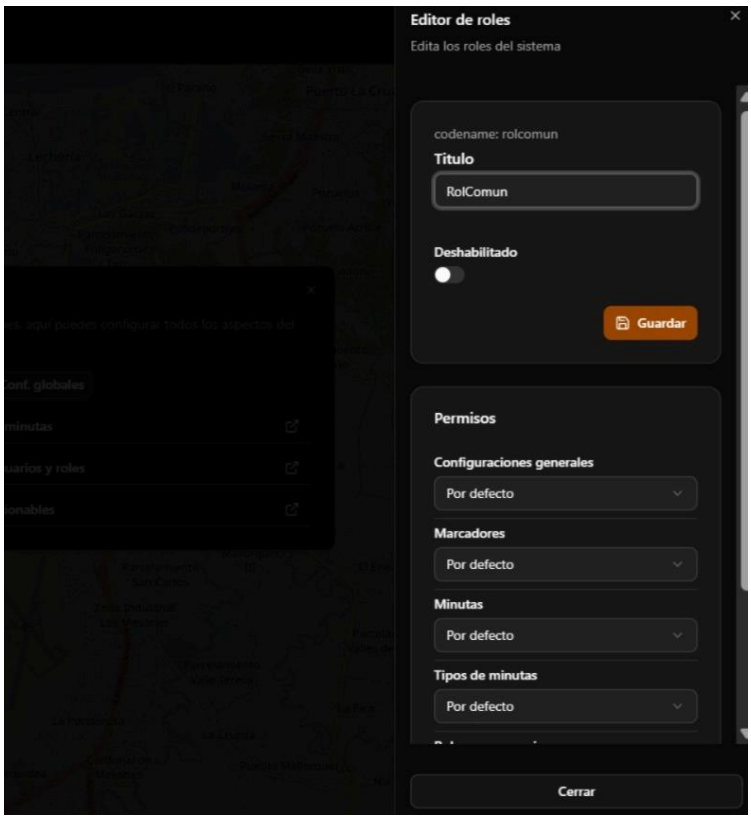

pueden realizar. Se organizan en categorías como "Configuraciones generales". Cada permiso tiene una casilla de verificación. Por ejemplo:

· Por defecto: Permiso básico.
· Marcadores: Permite crear, editar o eliminar puntos de riesgo.
· Minutas: Permite gestionar las minutas.
· Tipos de minutas: Permite administrar los diferentes tipos o plantillas de minutas.

6.4. Listas y Datos Seleccionables

Este módulo permite crear y gestionar listas desplegables que se usarán en otras partes del sistema (por ejemplo, para seleccionar un empleado, una urbanización, etc.).

Protección Civil y Administración de Desastres Municipal – Edif. Protección Civil Municipal, Calle Rosales, Sector Palotal, Detrás del Ambulatorio Ali Romero, Frente a la Circunscripción Militar del Estado Anzoátegui – Barcelona Edo Anzoátegui.
Teléfono: 02812770791 / Correo: pcadm.bolivar@gmail.com / pcbolivar.riesgos@gmail.com

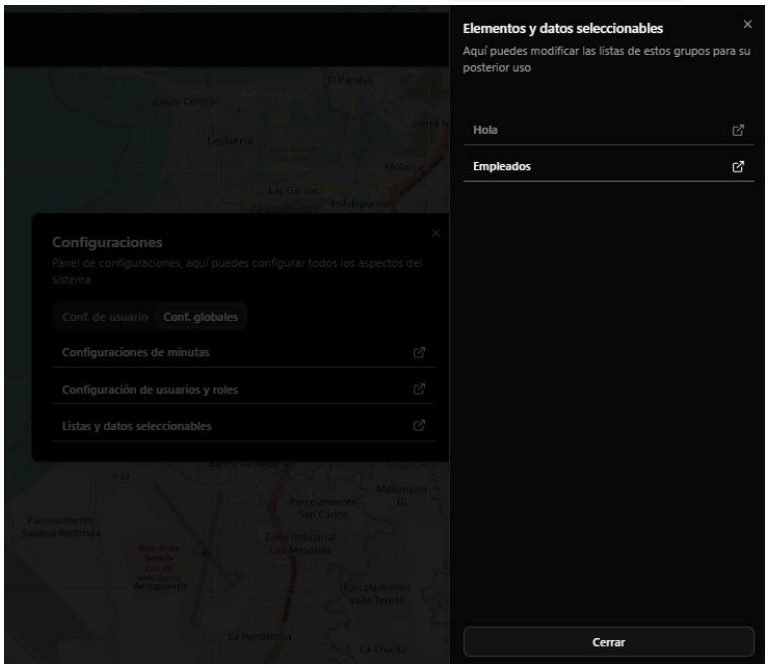

6.4.1. Orígenes (Grupos de Listas)

En la sección "Orígenes" puedes crear grupos de listas (IMG-20251025-WA0013.jpg).

· Haz clic en "Crear" para definir un nuevo grupo.
· Un grupo tiene un id (ej. "hola", "empleados").
· Un Título (ej. "Disponibilidad").
· Una lista de elementos, donde cada elemento tiene un nombre (ej. "Hola") y un estado de "Disponibilidad" (Habilitado/Deshabilitado).

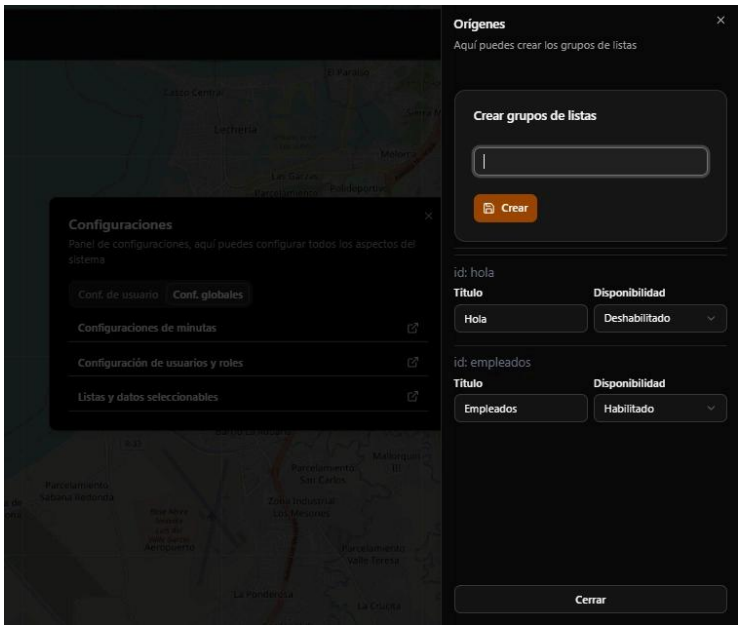

Protección Civil y Administración de Desastres Municipal – Edif. Protección Civil Municipal, Calle Rosales, Sector Palotal, Detrás del Ambulatorio Ali Romero, Frente a la Circunscripción Militar del Estado Anzoátegui – Barcelona Edo Anzoátegui.
Teléfono: 02812770791 / Correo: pcadm.bolivar@gmail.com / pcbolivar.riesgos@gmail.com

6.4.2. Gestión de Empleados

Parece haber una gestión específica para, que podría ser un tipo de "Origen". Aquí se listan los empleados con su id, Título (nombre), Valor (quizás cédula) y Disponibilidad. También hay un botón para [Crear] nuevos empleados.

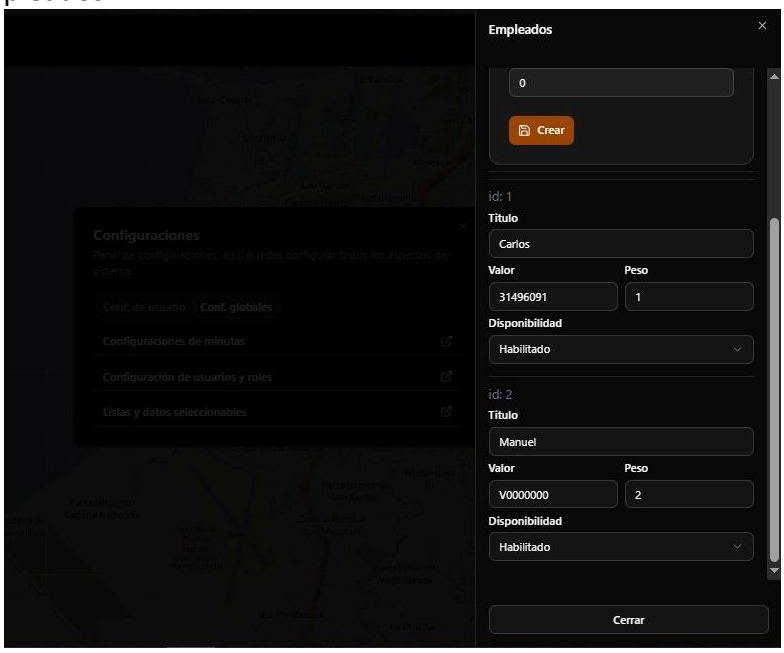

Protección Civil y Administración de Desastres Municipal – Edif. Protección Civil Municipal, Calle Rosales, Sector Palotal, Detrás del Ambulatorio Ali Romero, Frente a la Circunscripción Militar del Estado Anzoátegui – Barcelona Edo Anzoátegui.
Teléfono: 02812770791 / Correo: pcadm.bolivar@gmail.com / pcbolivar.riesgos@gmail.com

6.5. Editor de Plantillas de Minuta

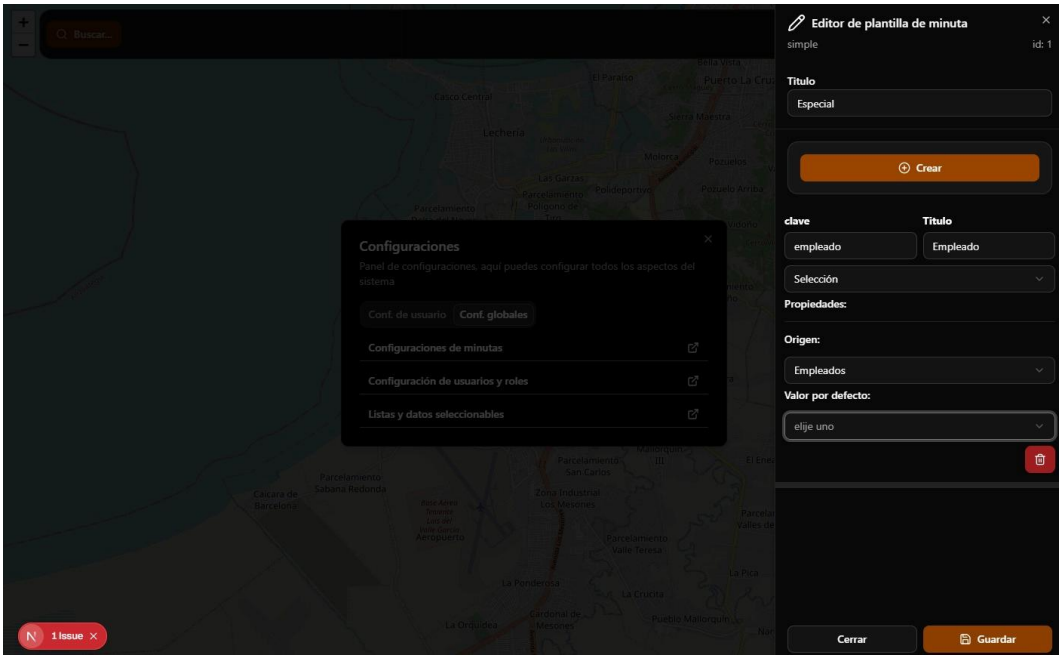

Para crear tipos de minuta personalizados (como la "Plantilla dirección" vista en la imagen), se utiliza el "Editor de plantilla de minuta".

6.5.1. Creación de una Nueva Plantilla

1. Accede al editor.
2. En la parte superior, puedes ver un identificador (simple, id: 1) y un campo para el "Título" de la plantilla (ej. "Especial", "Plantilla dirección").
3. Haz clic en "Crear" para empezar a definir la nueva plantilla.

6.5.2. Configuración de Campos de Plantilla

La parte inferior del editor permite definir los campos que tendrá la minuta. Cada campo tiene:

· Clave: El nombre interno del campo (ej. "empleado").
· Un selector de tipo de campo (probablemente "Selección", "Texto", "Número", etc.).
· Propiedades:
  · Origen: De dónde se obtienen los datos para este campo. Puede ser una lista predefinida (ej. "Empleados") o un tipo de dato.
  · Valor por defecto: El valor que aparecerá seleccionado por defecto (ej. "Carlos").
· Un botón para "Guardar" la configuración de la plantilla.

Protección Civil y Administración de Desastres Municipal – Edif. Protección Civil Municipal, Calle Rosales, Sector Palotal, Detrás del Ambulatorio Ali Romero, Frente a la Circunscripción Militar del Estado Anzoátegui – Barcelona Edo Anzoátegui.
Teléfono: 02812770791 / Correo: pcadm.bolivar@gmail.com / pcbolivar.riesgos@gmail.com

7. Generador de Estadísticas y Reportes

Este es el módulo para analizar la información cargada en el sistema. Se puede acceder desde el panel principal la opción se encuentra arriba del engranaje.

7.1. Acceso al Panel de Estadísticas

Una vez dentro del generador, verás un panel con un resumen y varias opciones. El panel se titula "Panel de generar las estadísticas y reportes del sistema".

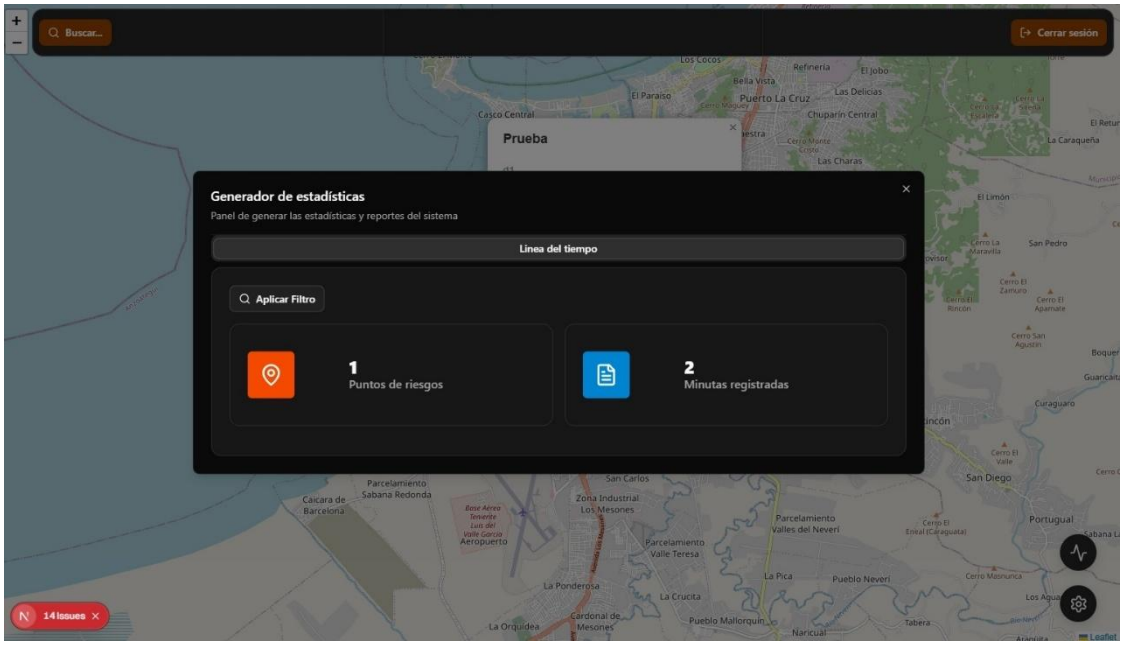

7.2. Resumen General y Ranking

La sección "Resumen general" suele mostrar un "Ranking de elementos más seleccionados", ofreciendo una visión rápida de los puntos, parcelamientos o tipos de incidencia más reportados.

Protección Civil y Administración de Desastres Municipal – Edif. Protección Civil Municipal, Calle Rosales, Sector Palotal, Detrás del Ambulatorio Ali Romero, Frente a la Circunscripción Militar del Estado Anzoátegui – Barcelona Edo Anzoátegui.
Teléfono: 02812770791 / Correo: pcadm.bolivar@gmail.com / pcbolivar.riesgos@gmail.com

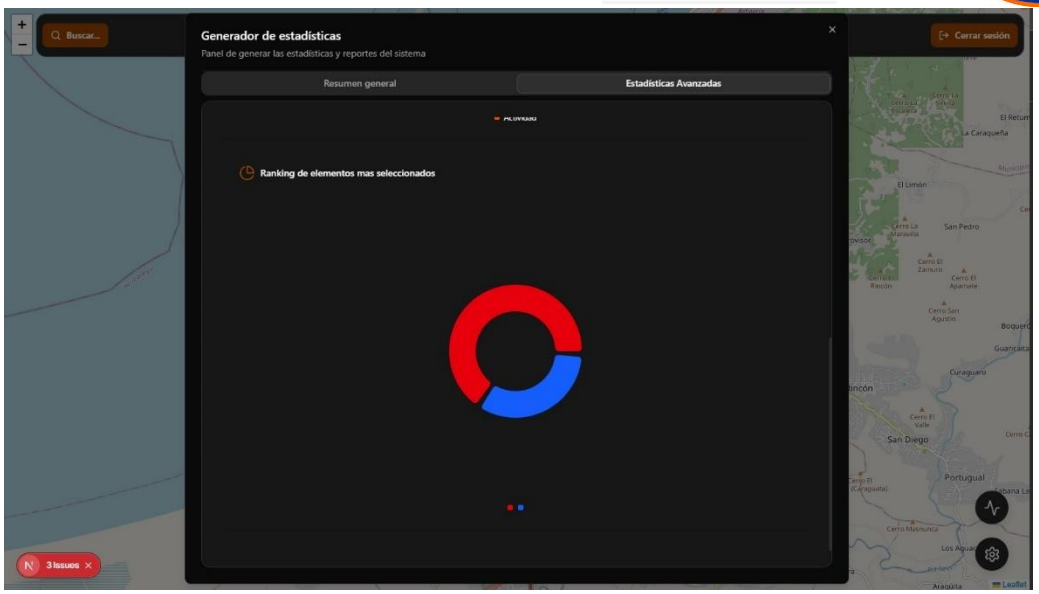

7.3. Línea del Tiempo y Filtros

La sección "Línea del tiempo" permite visualizar la actividad a lo largo del tiempo. Incluye:

· Un botón "Aplicar Filtro" para acotar la búsqueda por fechas u otros criterios.
· Métricas clave como "Puntos de riesgos" y "Minutas registradas", probablemente mostrando el total o la tendencia.

7.4. Estadísticas General y Avanzado

La pestaña o sección resumen general permite desglosar una gráfica de las minutas almacenadas mostrando el periodo del registro, sumatoria y promedio de costo.

Protección Civil y Administración de Desastres Municipal – Edif. Protección Civil Municipal, Calle Rosales, Sector Palotal, Detrás del Ambulatorio Ali Romero, Frente a la Circunscripción Militar del Estado Anzoátegui – Barcelona Edo Anzoátegui.
Teléfono: 02812770791 / Correo: pcadm.bolivar@gmail.com / pcbolivar.riesgos@gmail.com

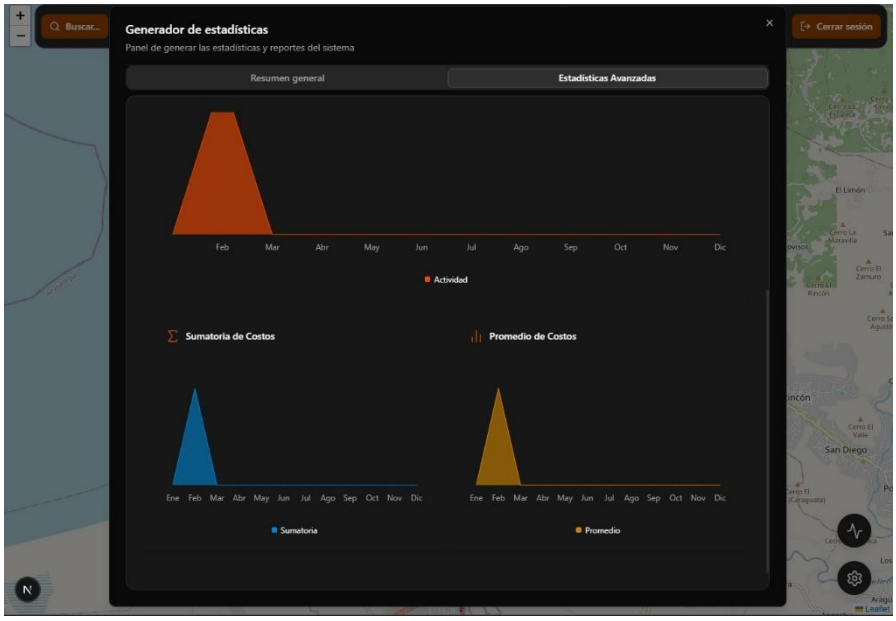

7.5. Análisis de Costos (Sumatoria y Promedio)

Para un análisis financiero, el sistema ofrece gráficos y tablas de costos (como se muestra en la imagen anterior).

· Se pueden visualizar la "Sumatoria de Costos" y el "Promedio de Costos" a lo largo de los meses del año (Ene, Feb, Mar...).
· Estos datos pueden presentarse en gráficos de barras o líneas para identificar tendencias y picos de gasto.

7.6. Tablas Recopilatorias de Minutas

Además de los resúmenes gráficos, el generador muestra tablas detalladas con los datos que alimentan las estadísticas tanto general como también avanzada. En las imágenes se observan dos tipos:

· Tabla de resumen mensual: Muestra, para meses como Agosto, Septiembre, etc., valores numéricos (probablemente conteo de minutas o sumatoria de costos) en dos columnas diferentes ("0 | 0"), quizás comparando dos métricas o períodos.
· Tabla detallada de minutas: Como las vistas en la sección 5.5, pero posiblemente filtradas según los criterios seleccionados en el panel de estadísticas.

Protección Civil y Administración de Desastres Municipal – Edif. Protección Civil Municipal, Calle Rosales, Sector Palotal, Detrás del Ambulatorio Ali Romero, Frente a la Circunscripción Militar del Estado Anzoátegui – Barcelona Edo Anzoátegui.
Teléfono: 02812770791 / Correo: pcadm.bolivar@gmail.com / pcbolivar.riesgos@gmail.com

La paginación en la parte inferior ("1 a 12 de 12 · Página 1 de 1") permite navegar a través de todos los registros.

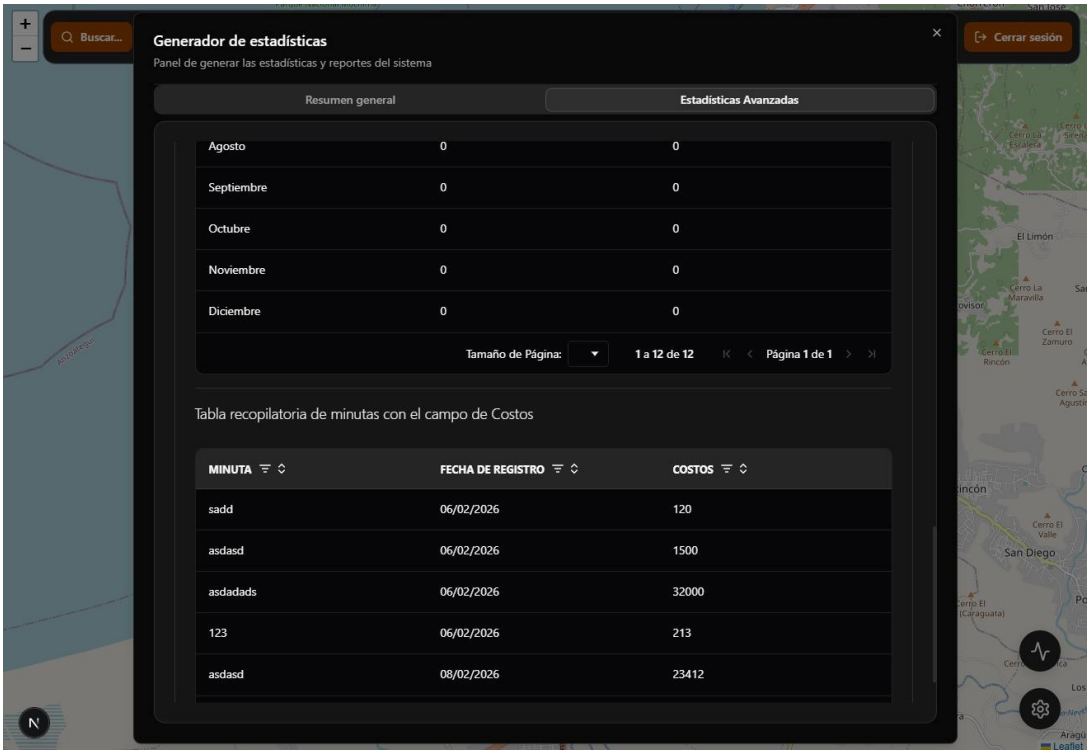

7.7.Reporte General y Avanzado

Por último el sistema puede generar reporte tanto general como avanzado en donde se encuentra las fechas, la estadística generada y una tabla con los títulos de la minutas almacenada.

Protección Civil y Administración de Desastres Municipal – Edif. Protección Civil Municipal, Calle Rosales, Sector Palotal, Detrás del Ambulatorio Ali Romero, Frente a la Circunscripción Militar del Estado Anzoátegui – Barcelona Edo Anzoátegui.
Teléfono: 02812770791 / Correo: pcadm.bolivar@gmail.com / pcbolivar.riesgos@gmail.com

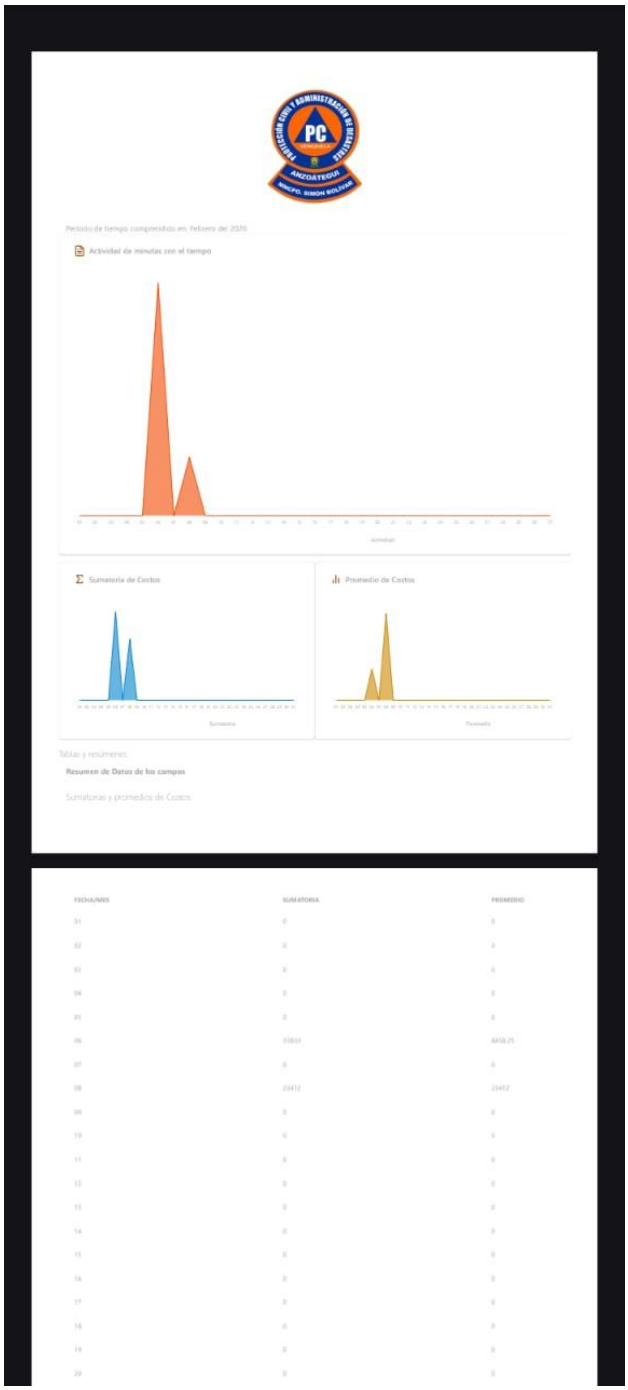

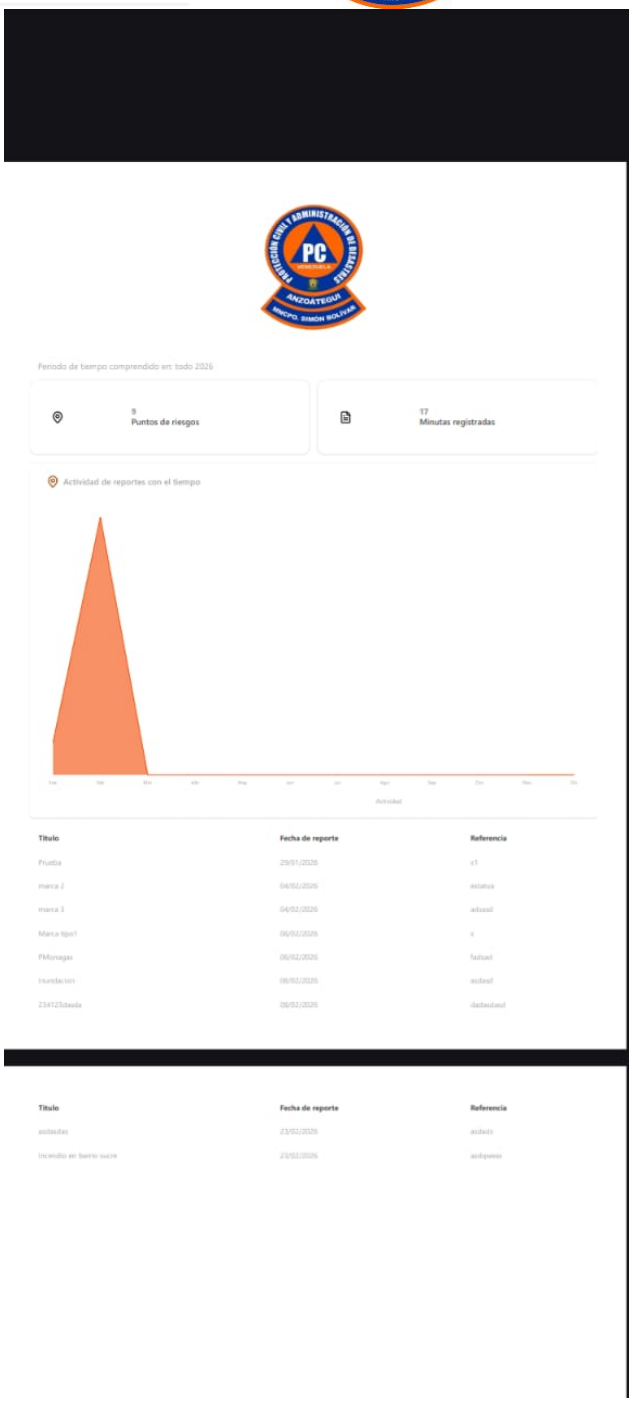

Protección Civil y Administración de Desastres Municipal – Edif. Protección Civil Municipal, Calle Rosales, Sector Palotal, Detrás del Ambulatorio Ali Romero, Frente a la Circunscripción Militar del Estado Anzoátegui – Barcelona Edo Anzoátegui.
Teléfono: 02812770791 / Correo: pcadm.bolivar@gmail.com / pcbolivar.riesgos@gmail.com